רשימת המפות ופירוט המקומות לבגרות

מספר יחידה	מספר מפה	תוכן המפה	שמות המקומות
1	1	תחום השליטה של ממלכת שלמה	יש לדעת את גודל הממלכה
1	2	ערים מרכזיות ששלמה בנה על דרך הים	חצור, מגידו, גזר
1	3	קשרי המסחר העיקריים של שלמה	ארם, צור, שבא, מצרים
2	4	המלכת רחבעם	שכם, ירושלים
2	5	ממלכת ישראל וממלכת יהודה	יש להכיר את גבולות ממלכת ישראל וממלכת יהודה
2	6	ממלכת ישראל - הצבת עגלי הזהב בדן ובבית אל	דן, בית אל
2	7	השתלטות בן הדד מלך ארם על צפון ממלכת ישראל	דן, אבל בית מעכה
2	8	ערי הבירה של ממלכת ישראל	פנואל, תרצה, שומרון, שכם
3	9	אליהו בזמן הבצורת	נחל כרית, צרפת
3	10	מעמד הר הכרמל	הר הכרמל, יזרעאל, שומרון
3	11	המקומות בהם עבר אליהו	נחל כרית, צרפת, הר הכרמל, יזרעאל, באר שבע, בית אל, גלגל, יריחו, הירדן * אין צורך להבדיל בין יריחו לגלגל.
4	12	ארם בימי ממלכות יהודה וישראל	ארם
4	13	מלחמת יורם בן אחאב ברמות גלעד (נגד ארם)	רמות גלעד, יזרעאל
4	14	ממלכת ישראל בימי ירבעם השני וממלכת יהודה בימי עזריה	יש לדעת את גודל הממלכות והדמיון לממלכה המאוחדת בימי שלמה
5	15	האימפריה האשורית	אשור
5	16	הגליית תושביה הצפוניים של ממלכת ישראל בימי פקח בן רמליהו	אבל בית מעכה, קדש, חצור, הגלעד, הגליל
5	17	הגליית ממלכת ישראל	אין צורך להכיר את המקומות הנזכרים אלא את מיקומה של האימפריה האשורית בלבד
6	18	אשור, בבל ומצרים (מותו של יאשיהו במגידו)	אשור, בבל, מצרים והעיר מגידו (מופיעה כבר במפה 2)
6	19	האימפריה הבבלית	בבל

מפה 1

מפה 2

מפה 3

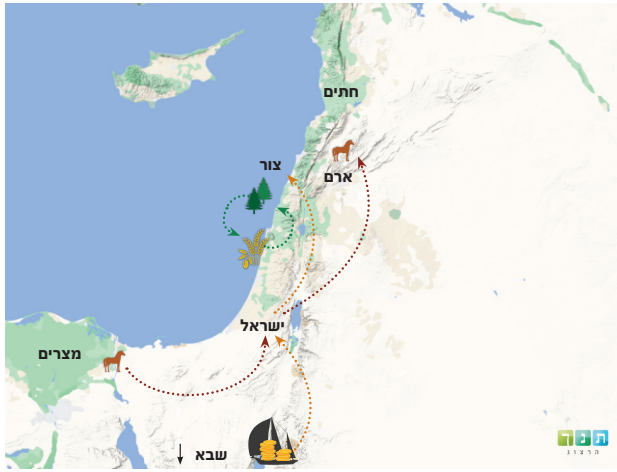

מפה 4

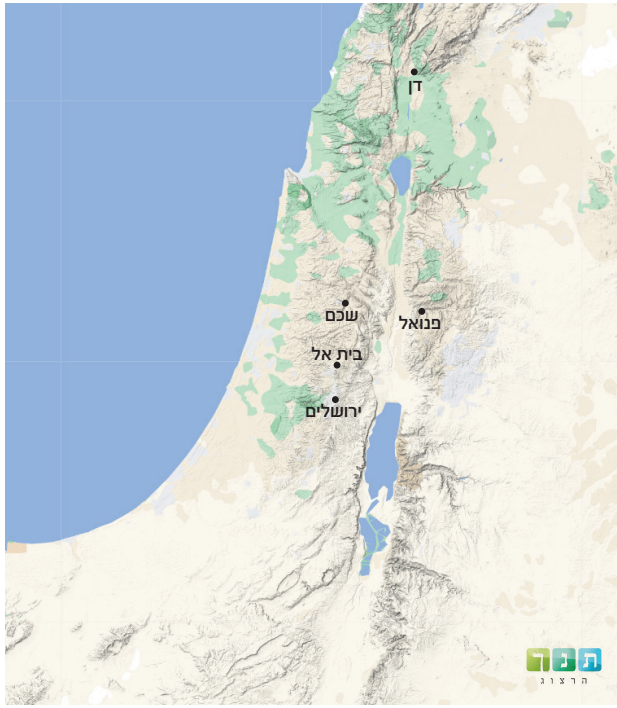

מפה 5

צידון
ארם
דן
ישראל
תרצה
שכם
פנואל
עמון
בית אל
ירושלים
פלשתים
יהודה
מואב
מצרים
אדום

מפה 6

ארם
דן
ישראל
תרצה
פנואל
שכם
בית אל
ירושלים
יהודה

מפה 7

עיון
אבל בית מעכה
דן
שבט נפתלי
כנרת
ארם
ישראל
תרצה
שכם
פנואל
בית אל
הרמה
מצפה
גבע בנימין
ירושלים

מפה 8

ארם
דן
ישראל
3
תרצה
4
שומרון
1
שכם
2
פנואל
בית אל
ירושלים

מפה 9

מפה 10

מפה 11

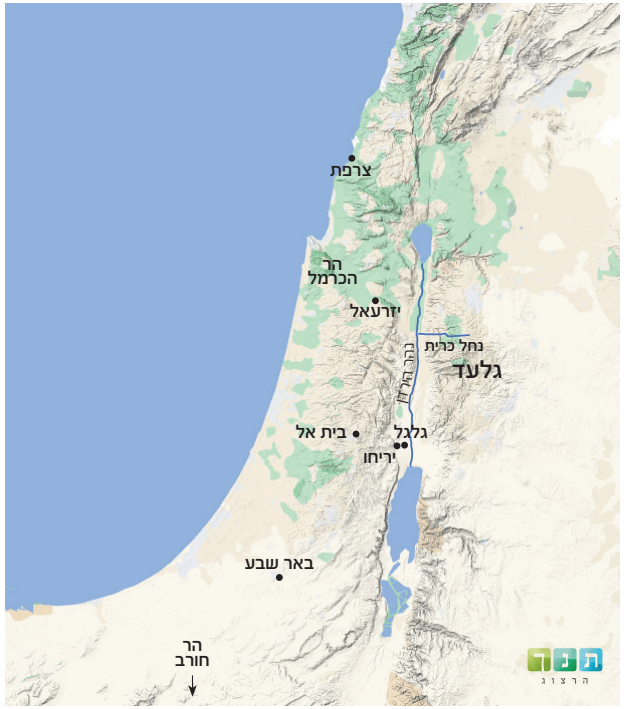
צרפת
הר הכרמל
יזרעאל
נחל כרית
גלעד
נחל יבוק
בית אל
גלגל
יריחו
באר שבע
הר חורב

מפה 12

דמשק
ארם
דן
רמות גלעד
ישראל
שומרון
בית אל
ירושלים
יהודה

מפה 13

ארם
רמות גלעד
יזרעאל
שומרון
ירושלים

מפה 14

לבא חמת
ארם
ישראל
שומרון
ירושלים
יהודה
מצרים
אדום
אילת

מפה 15

מפה 16

מפה 17

מפה 18

מפה 19